REPUBLIQUE TUNISIENNE
MINISTERE DE L'ENSEIGNEMENT SUPERIEUR
ET DE LA RECHERCHE SCIENTIFIQUE
UNIVERSITE TUNIS EL MANAR

FACULTE DES SCIENCES DE TUNIS
DEPARTEMENT DES SCIENCES DE L'INFORMATIQUE

RAPPORT DE PROJET DE
FONDEMENTS DE L'IA GLSI2 LCS2

TITRE

Optimisation d'évacuation d'un batiment

Réalisé par : **Ben Chaabene Ons**
Elea Gharbi
Chaari Yesmine

Encadré par : Mr.Lassoued Mohamed

Organisme d'accueil : FST – DSI

Contents

I. Introduction : 4
1) Présentation générale du sujet: 4
2) Contexte de l'évacuation en situation d'urgence: 4
3) Problématique: 4
4) Objectif du projet : 5
II. Cadre théorique : 5
1) Représentation d'un problème sous forme d'espace d'états: 5
2) Un espace d'états est défini par quatre éléments fondamentaux : 5
3) Présentation de l'algorithme BFS : 6
4) Principe des graphes et des grilles : 6
5) Justification du choix de BFS pour ce problème : 7
1) 7
III. Modélisation du problème : 8
1) Représentation du bâtiment sous forme de grille : 8
2) Définition des cellules : 8
3) Caractérisation des états et des contraintes : 8
4) Génération des déplacements autorisés : 9
5) Mise en oeuvre de l'algorithme BFS : 9
6) Recherche du plus court chemin : 9
IV. Conception et implémentation : 10
1) Langage et outils utilisés : 10
2) Structure générale du programme : 10
3) Description des principales fonctions: 11
V. Résultats expérimentaux : 12
1) Exemples de plans testés : ....**Error! Bookmark not defined.**
2) Chemins trouvés pour différents cas : ....**Error! Bookmark not defined.**
3) Affichage des résultats : ....**Error! Bookmark not defined.**
4) Nombre d'états explorés : ....**Error! Bookmark not defined.**
VI. Analyse et discussion : 16
1) Interprétation des résultats : 16
2) Avantages de BFS : 16

3) Limites de la solution :.....16
VII. Améliorations possibles : 17
1) Gestion de plusieurs personnes : 17
2) Gestion de plusieurs sorties : 18
VIII. Conclusion : 18
1) Résumé du projet 18
2) 2. Solution au problème 19
3) Avantages du projet : 19
4) Perspectives futures : 19

I. Introduction :

1) Présentation générale du sujet:

- L'évolution des technologies numériques a permis l'apparition de solutions intelligentes capables d'améliorer plusieurs domaines, notamment celui de la sécurité. Parmi ces technologies, l'intelligence artificielle occupe une place importante grâce à sa capacité à analyser un problème et à proposer rapidement une solution adaptée. Aujourd'hui, elle est utilisée dans plusieurs secteurs pour automatiser certaines tâches et faciliter la prise de décision.

-Dans le domaine de la sécurité, l'intelligence artificielle peut être appliquée aux plans d'évacuation numériques afin d'aider les personnes à quitter un bâtiment rapidement en cas d'urgence.
Ce projet s'inscrit dans cette perspective en proposant une solution basée sur l'IA pour déterminer le chemin le plus court vers une sortie à partir d'un plan simplifié représenté sous forme de grille.

2) Contexte de l'évacuation en situation d'urgence:

-Dans les situations d'urgence comme les incendies, les tremblements de terre ou les pannes critiques dans un bâtiment, il est essentiel de diriger rapidement les occupants vers les sorties de secours.
Les bâtiments comme les hôpitaux, les centres commerciaux ou les universités ont souvent de nombreux couloirs, escaliers et obstacles qui rendent l'évacuation difficile. Dans ces situations, chaque seconde est importante, et une mauvaise orientation peut aggraver les risques pour les personnes et les biens.
=> C'est pourquoi il est nécessaire de mettre en place un système qui aide les gens à évacuer. Grâce à l'intelligence artificielle, il est possible d'analyser rapidement l'environnement, de trouver les sorties et de montrer le chemin le plus court pour sortir.

3) Problématique:

- La problématique principale de ce projet consiste à déterminer comment aider efficacement une personne à quitter un bâtiment en danger en empruntant le chemin le plus court vers la sortie la plus proche. En effet, dans un environnement complexe, la présence de murs, d'obstacles ou de passages restreints rend la recherche manuelle d'un trajet optimal difficile. Il devient alors nécessaire de concevoir un système capable de représenter le bâtiment de manière simplifiée, d'identifier les zones accessibles et bloquées, puis de calculer automatiquement un chemin d'évacuation fiable. Alors ,comment modéliser un bâtiment et utiliser une méthode intelligente pour trouver rapidement le meilleur itinéraire d'évacuation en situation d'urgence ?

4) Objectif du projet :

-L'objectif de ce projet est de développer un système intelligent capable de calculer automatiquement le chemin d'évacuation le plus court dans un bâtiment. Pour cela, le bâtiment est modélisé sous forme d'une grille représentant un plan simplifié, où certaines cellules correspondent à des murs ou à des obstacles, tandis que d'autres représentent des couloirs ou des zones accessibles.

-À partir d'une position initiale donnée, le système doit déterminer le chemin optimal permettant d'atteindre la sortie la plus proche.

-Ce travail vise donc à combiner la modélisation d'un environnement avec une technique de recherche en intelligence artificielle afin d'améliorer la sécurité et de réduire les risques dans les situations critiques. Plus précisément, le projet met en œuvre l'algorithme BreadthFirst Search (BFS), connu pour sa capacité à trouver le plus court chemin dans un graphe non pondéré .

II. Cadre théorique :

-Notion d'intelligence artificielle appliquée à la recherche de chemin :

L'intelligence artificielle, dans le contexte de la recherche de chemin, consiste à permettre à un agent de trouver automatiquement une suite d'actions menant d'un point de départ à un objectif. Dans un labyrinthe ou une grille, l'agent doit analyser l'environnement, éviter les obstacles et choisir les déplacements possibles afin d'atteindre la destination.

1) Représentation d'un problème sous forme d'espace d'états:

En intelligence artificielle, tout problème de recherche peut être formalisé sous forme d'un espace d'états. Cette représentation permet de structurer le problème de manière exploitable par un algorithme.

2) Un espace d'états est défini par quatre éléments fondamentaux :

Elément	Définition	Application dans notre projet
État :	Une situation particulière du système	Une position (ligne, colonne) dans la grille
Etat initial :	Le point de départ	La cellule S (position de la personne)

État but :	L'objectif à atteindre	La cellule E (sortie)
Transitions :	Les actions possibles depuis un état	Déplacements : haut, bas, gauche, droite

=> Une transition entre deux états est valide si et seulement si :

La cellule destination existe dans la grille

La cellule destination n'est pas un mur #

La cellule destination n'a pas encore été visitée

3) Présentation de l'algorithme BFS :

BFS (Breadth-First Search) ou Parcours en Largeur est un algorithme de recherche qui explore un graphe niveau par niveau, c'est-à-dire qu'il visite d'abord tous les nœuds à distance 1 du départ, puis ceux à distance 2, et ainsi de suite.

Structure	Role
File (Queue)	Stocke les nœuds à explorer dans l'ordre FIFO
Visited	Ensemble des nœuds déjà visités, évite les cycles
Parents.	Dictionnaire qui mémorise le prédécesseur de chaque nœud pour reconstruire

Étapes de l'algorithme :

1-Mettre le nœud de depart dans la file.

2-Retirer le noeud de la sortie (de la tete) de la file pour l'examiner.

3-Mettre tous les voisins non examines a l'entrée (a la queue) de la file.

4-Si la file n'est pas vide reprendre à l'étape 2.

4) Principe des graphes et des grilles :

Un graphe est une structure composée de nœuds (sommets) et de liens (arêtes). Une grille est un cas particulier de graphe où les nœuds sont organisés sous forme de tableau. Chaque case de la grille représente un nœud, et les déplacements possibles définissent les connexions.

5) Justification du choix de BFS pour ce problème :

****Tableau comparatif des algorithmes de recherche**********

Critere	BFS	DFS	DLS
Optimalité	Oui	Non (il peut trouver un chemin plus long avant d'atteindre l'état but)	Non garentie
Mémoire	Elevée (doit stocker tous les états d'un niveau dans la file et la liste des visités)	Faible (ne stocke qu'un chemin en profondeur avec les états visités)	Faible car il stocke uniquement le chemin courant jusqu'à profondeur limite
Risque de boucle	Faible (puisque on utilise structure visited)	Elevé (peut entrer dans des boucles infinies si visites n'est pas utilisé)	Faible à modérer

A partir de ce tableau comparatif , il apparait clairement que l'algorithme BFS répond le mieux aux exigences de notre probleme :

Optimalité garantie :

-Lorsqu'il s'agit d'évacuer un bâtiment, chaque seconde est précieuse. La recherche en largeur d'abord, ou BFS, garantit que le premier chemin trouvé vers une sortie de secours est le plus court possible en termes de cases traversées.

-Puisque chaque déplacement dans la grille du bâtiment coûte le même (un déplacement coûte une case), la recherche en largeur d'abord s'assure que les occupants ne sont pas guidés par un itinéraire inutilement long, ce qui réduit le temps d'évacuation.

Complétude :

-Dans un bâtiment où certaines zones peuvent être bloquées par des obstacles, des portes fermées ou des couloirs inaccessibles, il est essentiel de savoir si une sortie est accessible ou non. La recherche en largeur d'abord est un algorithme complet.

-Si un chemin vers une sortie de secours existe, la recherche en largeur d'abord le trouvera. Et si aucun chemin n'est possible, elle le signalera clairement, permettant ainsi au système d'émettre une alerte ou de chercher une autre sortie.

Exploration systématique et sécurisée :

-Lors d'une évacuation, il est important de vérifier toutes les zones accessibles. La recherche en largeur d'abord explore le bâtiment de manière systématique, en commençant par les zones les plus proches, et en s'assurant que toutes les zones accessibles sont analysées avant de progresser plus loin. -Cette exploration approfondie garantit que la sortie la plus proche

est toujours identifiée en premier, même dans les configurations de bâtiment les plus complexes.

III. Modélisation du problème :

1) Représentation du bâtiment sous forme de grille :

-Le bâtiment est modélisé sous forme d'une **grille bidimensionnelle (2D)** Chaque cellule de cette grille représente une position possible dans le bâtiment.

-Cette représentation permet de transformer le problème réel (évacuation) en un **problème de recherche de chemin** dans un espace discret.

-La grille est implémentée JAVA sous forme d'une **liste de listes**, facilitant l'accès et la manipulation des cellules.

2) Définition des cellules :

Chaque cellule de la grille est caractérisée par un symbole spécifique :

Element	Description
S	Position de départ (personne à évacuer)
E	Sortie de secours
#	Mur ou obstacle (infranchissable)
.	Cellule libre (accessible)
*	Chemin trouvé (résultat final)

3) Caractérisation des états et des contraintes :

-Chaque état est représenté par un objet appelé Node.

Cet objet Node contient les coordonnées de la cellule, qui sont la ligne et la colonne, ainsi qu'une référence vers son état parent.

-Un déplacement vers un état voisin est considéré **comme valide** si trois conditions sont remplies :

a) La cellule ciblée doit exister dans la grille, ce qui signifie que ses indices doivent être dans les limites de la grille.

b)La cellule ne doit pas être un mur, ce qui est représenté par le symbole #.

c) La cellule ne doit pas avoir déjà été visitée, car cela permet d'éviter les cycles dans le chemin.

4) Génération des déplacements autorisés :

À partir de chaque état courant, le système génère les états successeurs en explorant ces quatre directions :

haut (-1.0) , bas(+1,0) , gauche (0,-1) , droite (0,+1)

5) Mise en oeuvre de l'algorithme BFS :

Etapes de l'algorithme

1)Initialiser la file avec le nœud de départ S

2)Marquer S comme visité

3)Tant que la file n'est pas vide :

Extraire le nœud en tête de file

Si ce nœud est une sortie E → chemin trouvé

Sinon, générer ses voisins valides et non visité les marquer comme visités et les ajouter à la file

4)Si la file est vide sans avoir trouvé de sortie → aucun chemin possible

6) Recherche du plus court chemin :

-Une fois que nous avons atteint la sortie, nous reconstruisons le chemin optimal en remontant la chaîne de parents. Nous partons du noeud de sortie et remontons jusqu'au noeud de départ.

Ensuite, nous inversons le chemin pour le présenter correctement, en allant du départ vers la sortie.

IV. Conception et implémentation :

1) Langage et outils utilisés :

-Eclipse :

C'est un environnement de développement intégré (IDE) open source principalement utilisé pour la programmation, notamment en Java, mais aussi dans d'autres langages via des extensions. Il fournit un ensemble d'outils permettant d'écrire, compiler, exécuter et déboguer du code dans une interface unique. Eclipse facilite également la gestion des projets logiciels grâce à ses fonctionnalités d'organisation, d'autocomplétion et de support des plugins.

- java :

Java est une technique informatique développée initialement par Sun Microsystems puis acquise par Oracle à la suite du rachat de l'entreprise

-Fxjava :

JavaFX est une bibliothèque et un framework de Java utilisé pour développer des interfaces graphiques (GUI). Il permet de créer des applications desktop interactives avec des composants visuels tels que les boutons, les champs de texte, les tableaux et les menus.

2) Structure générale du programme :

-2D / 3D :

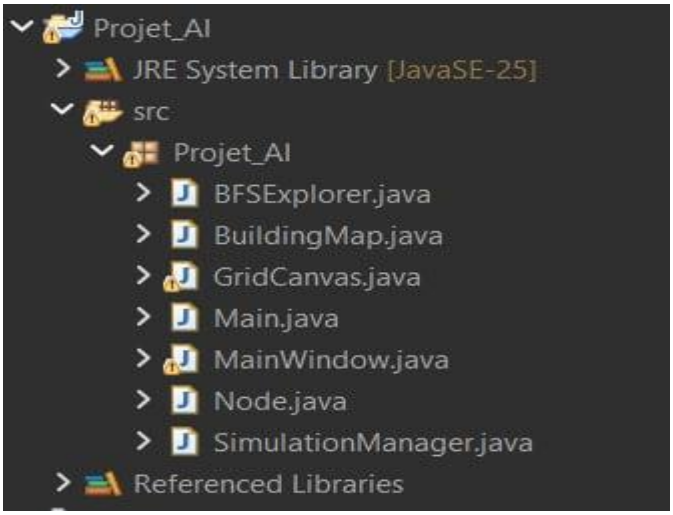

-

Classe	Description

MainWindow	Gère la fenetre principale , les panneaux de contrôle , les boutons d'action et la barre de progression
GridCanvas	Dessiner la grille , les agents et le chemins de manière performante
BuildingMap	Stocker et manipuler d'accès sécurisées des cellules
BFSExplorer	Implementer l'algorithme BFS pour trouver le chemin le plus court vers une sortie

3) Description des principales fonctions:

-Chargement des scénarios pré-définis :
L'utilisateur peut choisir parmi plusieurs plans de batiments via un menu déroulant .

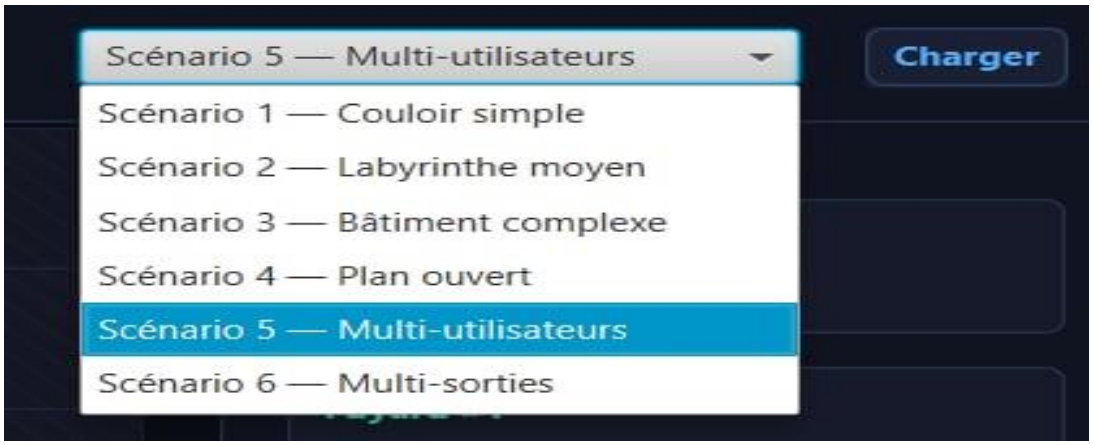

-Edition dynamique de la grille :
Une fonctionnalité permet à l'utilisateur de modifier la carte en temps réel par l'ajout ou suppression de murs .

-Statistiques des agents :

Affichage de données précises (Nœuds explorés et distance parcourue) pour chaque agent présent sur la carte .

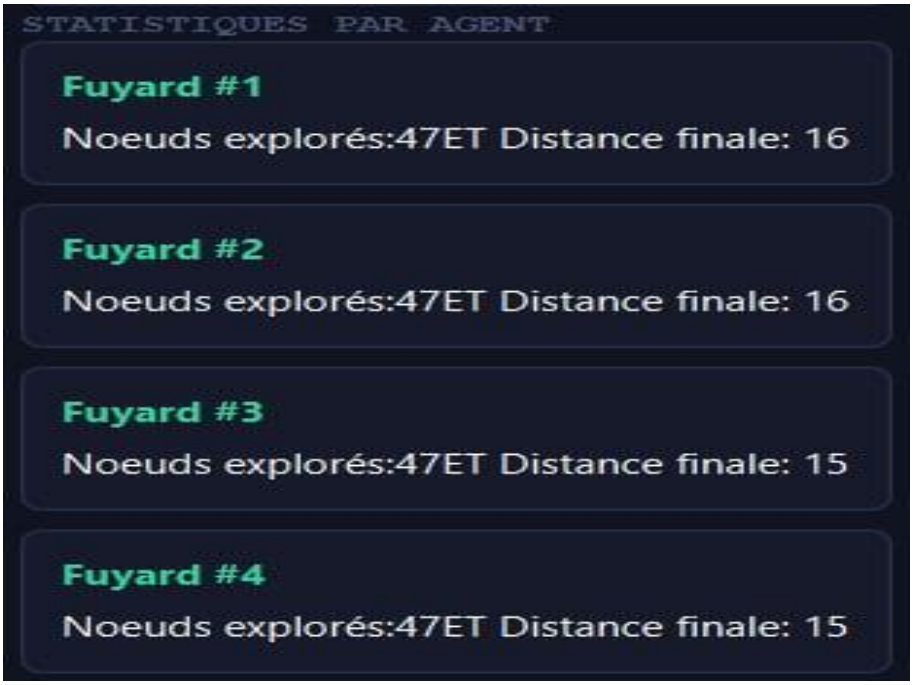

-Moteur de simulation et pathfinding :

Calcul automatique du chemin le plus court entre les points de départ et les sorties de secours.

V. Résultats expérimentaux :

6) Exemples de plans testés :

Afin d'évaluer les performances de l'algorithme BFS, plusieurs scénarios de plans ont été testés, notamment :

- Un couloir simple (2D)
- Un environnement avec obstacles
- Une structure en 3D simulant un bâtiment réel

Ces différents cas permettent d'analyser le comportement de l'algorithme dans des situations variées.

6) Chemins trouvés pour différents cas

L'algorithme BFS garantit la recherche du **chemin le plus court** entre le point de départ (S) et la sortie (E), lorsque celui-ci existe.

Dans le cas du couloir simple :

- Le chemin optimal est trouvé rapidement

- Le nombre d’étapes correspond à la distance minimale

Dans le cas 3D :

- L’algorithme explore plusieurs directions
- Il peut arriver qu’aucun chemin ne soit trouvé (sortie isolée)

6) Affichage des résultats :

Pour la partie consol :

```
=== Fuyard #1 ===
Noeud exploré : (1,1) | profondeur = 0
Noeud exploré : (2,1) | profondeur = 1
Noeud exploré : (1,2) | profondeur = 1
Noeud exploré : (3,1) | profondeur = 2
Noeud exploré : (1,3) | profondeur = 2
Noeud exploré : (4,1) | profondeur = 3
Noeud exploré : (2,3) | profondeur = 3
Noeud exploré : (1,4) | profondeur = 3
Noeud exploré : (4,2) | profondeur = 4
Noeud exploré : (3,3) | profondeur = 4
Noeud exploré : (1,5) | profondeur = 4
Noeud exploré : (4,3) | profondeur = 5
Noeud exploré : (2,5) | profondeur = 5
Noeud exploré : (1,6) | profondeur = 5
Noeud exploré : (4,4) | profondeur = 6
Noeud exploré : (3,5) | profondeur = 6
Noeud exploré : (1,7) | profondeur = 6
Noeud exploré : (3,6) | profondeur = 7
Noeud exploré : (2,7) | profondeur = 7
Noeud exploré : (1,8) | profondeur = 7
Noeud exploré : (3,7) | profondeur = 8
Noeud exploré : (1,9) | profondeur = 8
Noeuds explorés : 22
----------------
```

Figure 1 : Résultat d’exécution dans la console

Description à mettre :
Cette figure montre les étapes d’exploration de l’algorithme BFS dans la console.
Chaque ligne correspond à un nœud visité avec :

- ses coordonnées (ligne, colonne)
- sa profondeur (distance depuis le point de départ)

On observe que :

- L’exploration se fait niveau par niveau
- Le nombre total de nœuds explorés est affiché à la fin (ici : 22)

Pour la partie de 2D :

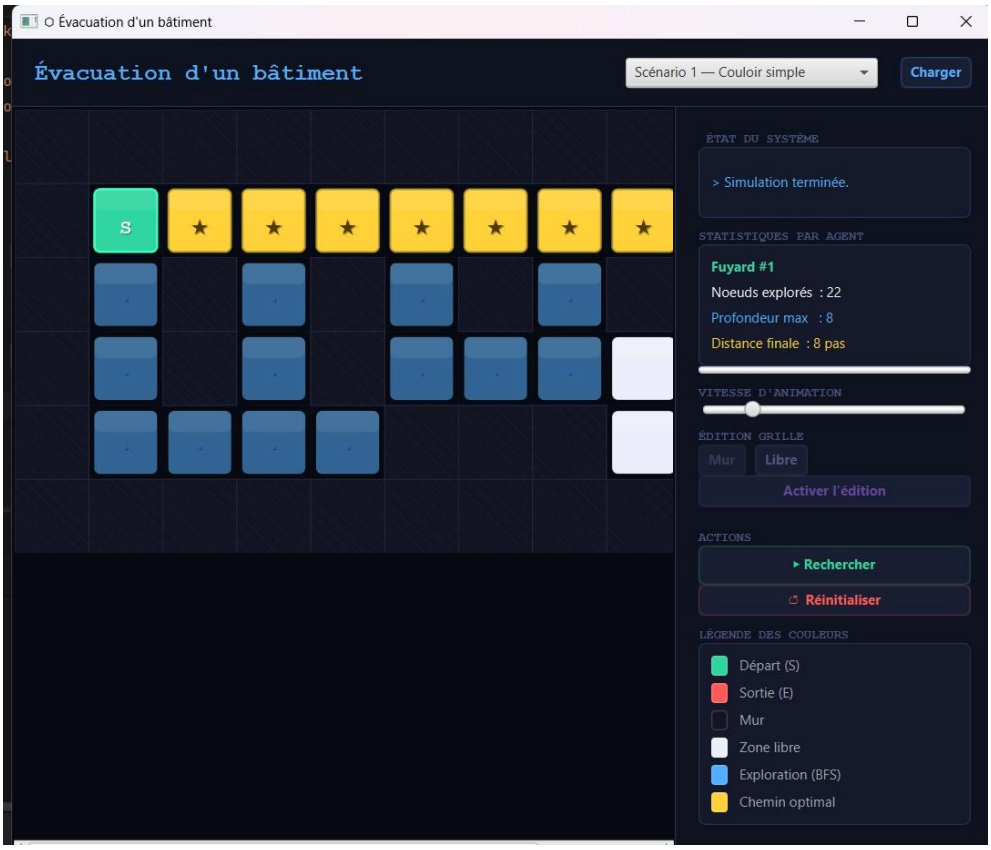

Figure 2 : Visualisation 2D du parcours BFS

Description à mettre :
Cette figure représente l'exécution de l'algorithme BFS dans une grille 2D.

Les éléments sont codés par couleur :

On remarque que :

- BFS explore progressivement toutes les directions possibles
- Le chemin optimal est clairement affiché en jaune
- Les statistiques indiquent :

Pour la partie de 3D :

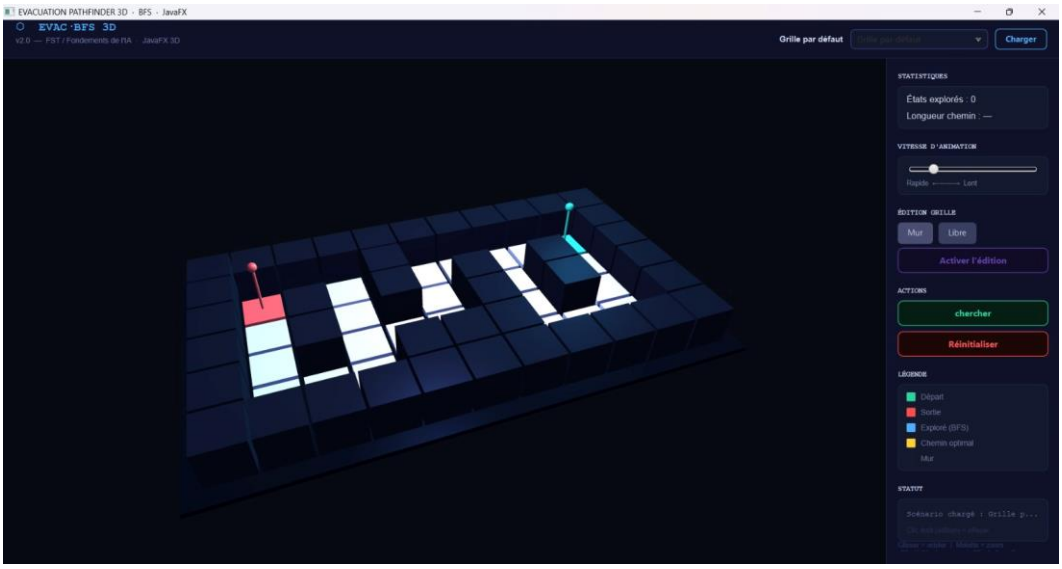

Figure 3 : Simulation 3D du bâtiment

Description à mettre :
Cette figure illustre une simulation en 3D de l'évacuation d'un bâtiment.

Caractéristiques :

- Représentation réaliste des murs et des chemins
- Visualisation interactive (rotation, zoom)
- Départ et sortie représentés en 3D

Observation :

- Dans cet exemple, aucun chemin n'est trouvé vers la sortie
- Cela montre un cas réel où BFS explore sans succès
- Le nombre d'états explorés reste faible (0 ici avant lancement)

VI. Analyse et discussion :

1) Interprétation des résultats :

Les résultats obtenus montrent que l'algorithme BFS :

- Trouve toujours un chemin lorsqu'il existe
- Garantit le plus court chemin
- Fonctionne correctement dans différents scénarios

Donc L'algorithme est fiable pour la résolution du problème d'évacuation.

2) Avantages de BFS :

L'utilisation de BFS présente plusieurs avantages :

- Garantie du plus court chemin
- Facile à implémenter
- Adapté aux grilles non pondérées
- Exploration systématique

D'où C'est un choix pertinent pour ce type de problème.

3) Limites de la solution :

Malgré ses avantages, BFS présente certaines limites :

- Consomme beaucoup de mémoire
- Explore beaucoup d'états inutiles
- Moins efficace pour de grandes grilles

Cas où l'algorithme est moins efficace :

BFS devient moins performant dans les cas suivants :

- Grilles très grandes
- Nombre élevé d'obstacles
- Environnement complexe (labyrinthe dense)

VII. Améliorations possibles :

1) Gestion de plusieurs personnes :

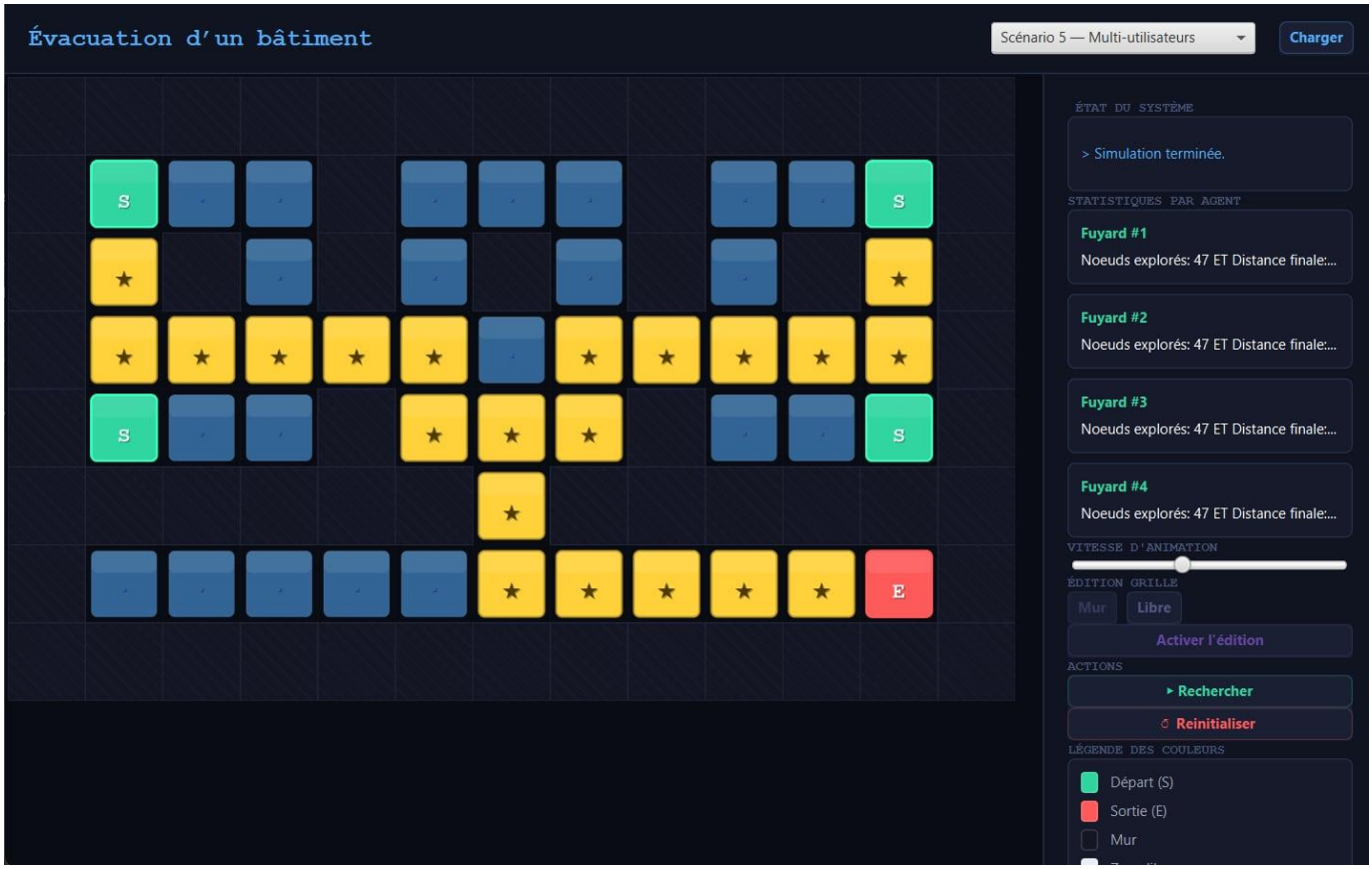

Analyse : on lit "Nœuds explorés 47".

Interprétation : Ce chiffre représente la taille de l'arbre de recherche développé avant d'atteindre la sortie.

Observation :

-On remarque que pour des agents partant de points différents vers la même sortie, le nombre de nœuds explorés varie selon la position initiale. Cela illustre la complexité $O(V + E)$ où V est le nombre de cases libres et E les transitions possibles.

-Plus l'agent est loin, plus la structure de données (la file) doit stocker de nœuds avant d'aboutir.5.

- Reconstruction du Chemin (Backtracking) une fois la sortie (E) atteinte, on observe le tracé immédiat du chemin optimal.

2) Gestion de plusieurs sorties :

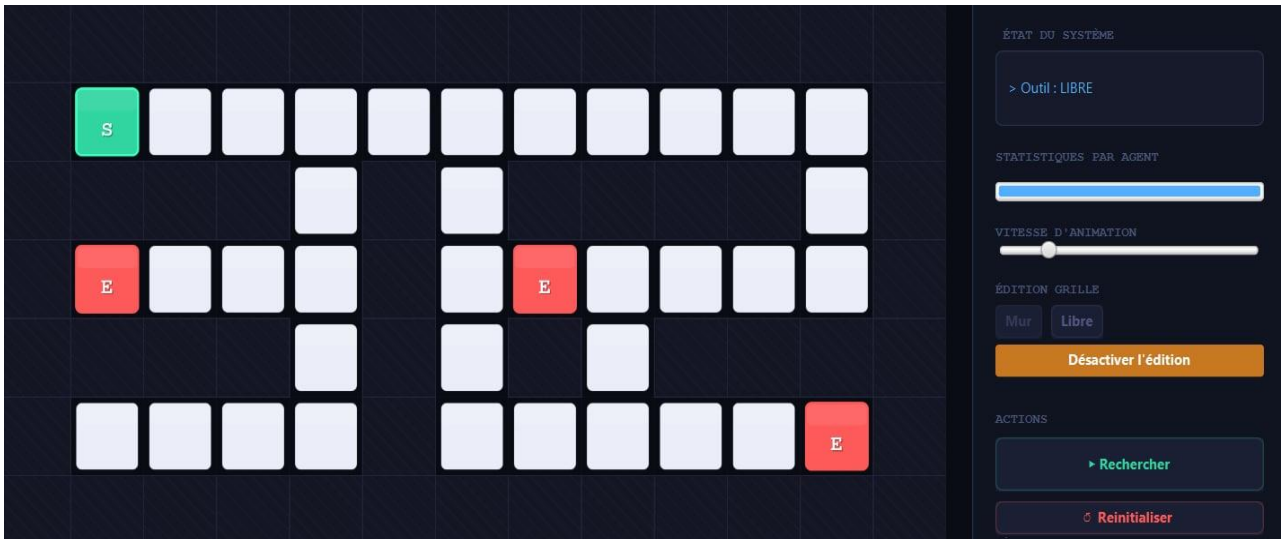

Analyse et observation :

- Le BFS n'a pas besoin de savoir quelle sortie est la meilleure. En explorant "en cercle" autour du départ (S), il frappera naturellement la sortie (E) la plus proche en premier.

-Lors de l'éxecution on observe ces 3 mécanismes :

- Arrêt immédiat: Dès qu'une branche de l'onde d'exploration touche n'importe quelle sortie, l'algorithme s'arrête. Cela garantit que l'agent prend le chemin le plus court vers l'issue de secours la plus accessible.

- Évitement des sorties lointaines : Les sorties plus éloignées (comme celle en bas à droite sur ton image) sont ignorées car le BFS trouve une solution plus courte avant même d'avoir fini d'explorer le reste de la carte.

- Optimisation du flux : Cette fonctionnalité simule parfaitement un comportement de survie logique : un individu cherche l'issue la plus rapide pour quitter le bâtiment, réduisant ainsi le temps d'exposition au danger.

VIII. Conclusion :

1) Résumé du projet

-Notre projet consistait à créer une application pour simuler l'évacuation d'urgence dans les bâtiments. Nous avons conçu une architecture solide qui sépare la logique de l'algorithme de recherche du graphique. L'application permet non seulement de simuler les chemins de

fuite, mais offre aussi une grande flexibilité grâce à un outil d'édition de cartes en temps réel.

2) 2. Solution au problème

-Le projet répond bien au défi de l'évacuation rapide : l'utilisation de l'algorithme de recherche en largeur garantit que nous trouvons toujours le chemin le plus court vers la sortie la plus proche.
- Le système gère bien les configurations complexes, comme les murs et les impasses, et les scénarios avec plusieurs sorties, ce qui nous permet de prendre des décisions fiables en situation de crise.

3) Avantages du projet :

- Sur le plan **technique** : nous avons amélioré nos compétences en structures de données, comme les files d'attente et les matrices, et en techniques de rendu graphique performantes.

- Sur le plan **ergonomique** : nous avons créé une interface utilisateur intuitive et facile à utiliser, qui permet à tout le monde d'analyser des données complexes.

- Sur le plan **pédagogique** : l'application permet de visualiser étape par étape comment l'algorithme fonctionne, ce qui en fait un excellent outil pour apprendre la sécurité.

4) Perspectives futures :

-Bien que le BFS soit optimal en termes de distance pour des graphes non pondérés, une évolution majeure serait l'implémentation de l'algorithme A* (A-Star).
Et voici un tableau comparatif qui montre la valeur de A* :

Caractéristique	BFS	A*
Type de recherche	Recherche«aveugle »	Recherche »guidée »
Stratégie	Explore toutes les directions par vagues circulaires	Utilise une estimation de la distance pour viser la cible

Rapidité	Plus lent sur de grandes cartes	Très rapide , meme sur des cartes vastes
Efficacité	Gaspillage de ressources : il visite des cases qui n’ont pas aucune chance d’etre dans le bon chemin	Econome : il ne visite que les cases qui le rapprochent de la sortie
Cout CPU/RAM	Tres lourd sur de grandes cartes (la file d’attente explose)	Tres leger (ne stocke que le strict nécessaire)

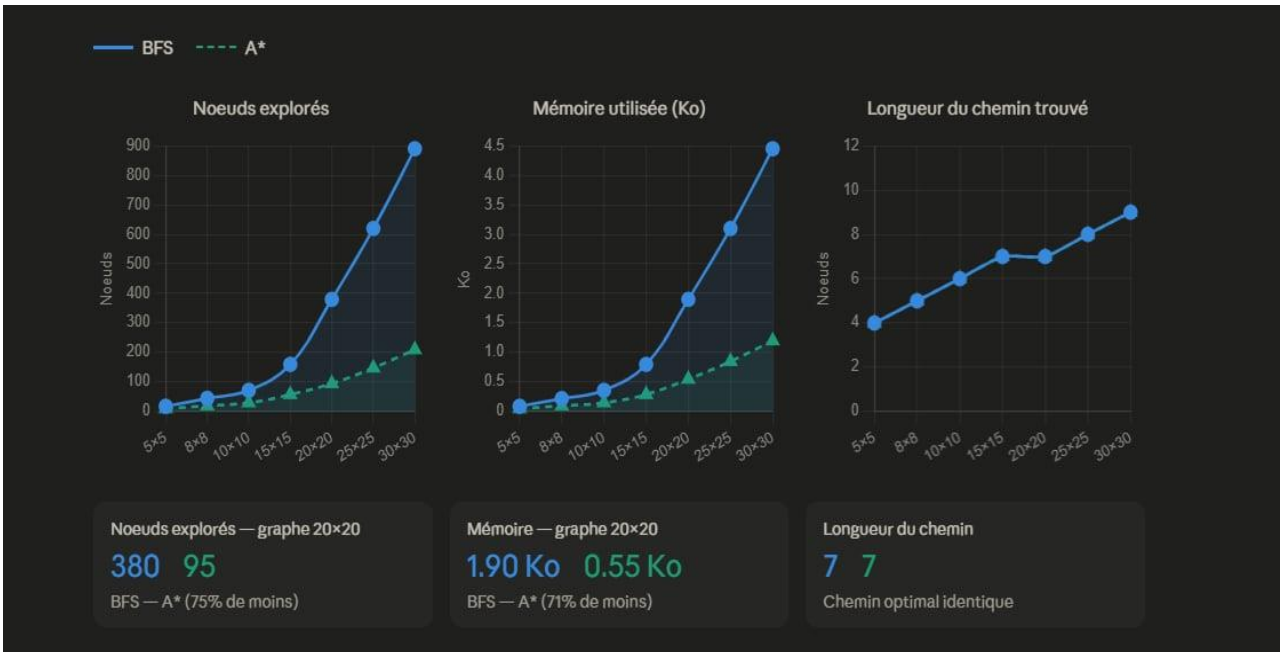

- Cette analyse comparative démontre que l'algorithme A* surpasse nettement le BFS en termes d'efficacité, en réduisant le nombre de nœuds explorés de 75 % tout en garantissant un chemin optimal identique. Ces résultats confirment que l'intégration du A* est l'évolution indispensable pour optimiser les ressources système et permettre des simulations fluides dans des environnements vastes et complexes.